T.C.
KÜLTÜR VE TURİZM BAKANLIĞI
Kültür Varlıkları ve Müzeler Genel Müdürlüğü

27.
ARAŞTIRMA SONUÇLARI TOPLANTISI
3. CİLT

25-29 MAYIS 2009
DENİZLİ

T.C. Kültür ve Turizm Bakanlığı Yayın No : 3250/3
Kültür Varlıkları ve Müzeler Genel Müdürlüğü Yayın No: 143/3

YAYINA HAZIRLAYANLAR
Dr. Haydar DÖNMEZ
Candaş KESKİN

Kapak ve Uygulama
Necdet ÇELİKTAŞ

ISSN: 1017-7663

Kapak Fotoğrafı: *Harun ÖZDAŞ*
"Ege-Akdeniz Bölgesi Sualtı Araştırması 2008 Yılı Çalışmaları"
"Datca Yarımadası Gazze batığı sepet formlu amphoralar"

Not : Araştırma raporları, dil ve yazım açısından Klâsik Filolog Dr. Haydar Dönmez tarafından denetlenmiştir. Yayımlanan yazıların içeriğinden yazarları sorumludur.

İsmail Aygül Ofset Matbaacılık
San. Tic. Ltd. Şti.
ANKARA-2010

İÇİNDEKİLER

Ender VARİNLİOĞLU, Pierre DEBORD
2008 Yılı Karia Araştırmaları 1

Martin BACHMANN
2008 Yılı Oinoanda Çalışmaları 9

Hamdi ŞAHİN
Dağlık Kilikia Yerleşim Tarihi ve Epigrafya Araştırmaları 2008 17

Hugh ELTON, John HALDON , Jim NEWHARD , Sean LOCKWOOD
Avkat Archaeological Project, 2007-2008 29

Emel ERTEN, Murat ÖZYILDIRIM, Tuna AKÇAY
Olba 2008 Yılı Yüzey Araştırması 51

Füsun TÜLEK
Osmaniye Arkeolojik Yüzey Araştırması 2008 Yılı Çalışması 69

Peter RUGGENDORFER
Die Ergebnisse Der Feldforschungen in Alinda 2008 83

Ümit AYDINOĞLU
Erdemli Ve Silifke Arasında Kentleşme ve Tarımsal Organizasyon
2008 Yılı Araştırması 97

S. MAZZONI , A. D'AGOSTINO , V. ORSI
Kuşaklı 2008 Survey Season (Yozgat-Sorgun) 1st Preliminary Report 109

Atilla ENGİN
Sivas İli 2008 Yılı Yüzey Araştırması 129

A. Osman UYSAL
Çanakkale İli Ortaçağ ve Türk Dönemi Yüzey Araştırması (2008) 151

Mustafa ŞAHİN, İ. Hakan MERT, Derya ŞAHİN
Keles Yüzey Araştırması, 2008 163

Mustafa ŞAHİN, Serkan GÜNDÜZ
Kyzikos Sualtı Araştırması , 2008 179

Karl ST ROBEL, Christian GERBER, Gabriele KOINER
Uluslararası Tavium Projesi: 2008 Yılı Araştırmaları 187

Günder VARİNLİOĞLU
Geç Antik Dönemde Silifke Kırsalında Yerleşim:
2002-2007 Yılları Yüzey Araştırması Sonuçları 201

Winfried HELD, Gonca CANKARDAŞ ŞENOL, Ahmet Kaan ŞENOL
2008 Yılı Bybassos Araştırması 215

Harun TAŞKIRAN, Metin KARTAL
2008 Yılı Ilısu Baraj Gövdesi Alanı Yüzey Araştırması 233

Poul PEDERSEN
Report of The Turkish-Danish Investigations at
Ancient Halikarnassos (Bodrum) in 2008 245

Kadir PEKTAŞ, Gülsen BAŞ
Bitlis ve Çevresi Yüzey Araştırması, 2008 259

Şengül AYDINGÜN, Emre GÜLDOĞAN, Volker HEYD, Hakan ÖNİZ
2008 Yılı İstanbul Tarih Öncesi Çağlar Yüzey Araştırması 273

Enver AKIN
Adıyaman Gaziantep ve Şanlıurfa Müzeleri'nde Yer Alan
Roma Dönemi Ticaret Malları 289

Fikri KULAKOĞLU, Kutlu EMRE, Ryoichi KONTANİ, Hiroomi TS UMURA, Sabahattin EZER
Kayseri Arkeolojik Yüzey Araştırması Projesi (Kayap)
2008 Yılı Çalışmaları Sonuç Raporu 305

Ann E. KILLEBREW, Gunnar LEHMANN
Summary of the 2008 Cilicia Survey (İskenderun Bay Region) 319

İsa KIZGUT
Beydağları Yüzey Araştırmaları 2008 339

Abuzer KIZIL, İsmail Ernur ÖZTEKİN
2008 Yılı Muğla İli, Milas İlçesi İle Ören ve Selimiye Beldeleri'nde
Arkeolojik Yüzey Araştırması 359

Gülçin İLGEZDİ BERTRAM, Jan-K. BERTRAM
İlk Tunç Çağı Ankara Bölgesi Araştırmaları (Odtü Yüzey Araştırması 2008 ve Ahlatlıbel Buluntuları)
Zur Frühbronzezeit in Der Ankara-Region (Odtü-Survey 2008 und Aufarbeitung Der Ahlatlıbel-Funde) 385

Ferudun ÖZGÜMÜŞ
2008 Yılı İstanbul Sur İçi Arkelojik Çalışmaları 397

Hasan BAHAR
Konya ve Karaman İlleri ve İlçelerinde Arkeolojik Yüzey Araştırması, 2008 415

Osman AYTEKİN
Artvin-Erzurum İlleri Çoruh Vadisi'ndeki Tarihî Yollar ve Kültür Varlıkları Yüzey Araştırması, 2008 435

Tunç SİPAHİ, Tayfun YILDIRIM
2008 Yılı Çankırı ve Çorum İlleri Yüzey Araştırması 447

Michael HOFF, Rhys TOWNSEND, Ece ERDOĞMUŞ
The Antiocheia Ad Cragum Archaeological Research Project: Northeast Temple 2008 Season 461

KAYSERİ ARKEOLOJİK YÜZEY ARAŞTIRMASI PROJESİ (KAYAP) 2008 YILI ÇALIŞMALARI SONUÇ RAPORU

Fikri KULAKOĞLU*
Kutlu EMRE
Ryoichi KONTANİ
Hiroomi TSUMURA
Sabahattin EZER

I. AraştırmaTarihçesi

Kayseri İli, Kocasinan İlçesi sınırları içinde yer alan Kültepe'de, 1948 yılından itibaren bilimsel sistematik kazılar sürdürülmektedir. T. Özgüç başkanlığındaki kazı ekibi, sadece Kültepe değil, aynı zamanda Kültepe'nin etrafında yer alan çok çeşitli kültürlere ait tarihî anıtları ve ören yerlerini de incelemiş, bunları bilim dünyasına tanıtmıştır.

T. Özgüç başkanlığındaki ekip, Kayseri İli sınırları içindeki M.Ö. II. binyıla ait yerleşim yerlerinde ve özellikle Hitit kaya anıtlarında araştırmalar gerçekleştirmiştir. Bölgedeki ilk çalışmalar Kayseri'nin ve Erciyes Dağı'nın hemen güneyindeki Fraktin Hitit kaya kabartması ve anıtın yerleşim yeri olan Fraktin Höyük'te gerçekleştirilmiştir[1]. Daha sonraki dönemlerde, bölgedeki

* Prof. Dr. Fikri KULAKOĞLU, Ankara Üniversitesi DTCF Protohistorya ve Önasya Arkeolojisi Anabilim Dalı Sıhhiye/Ankara 06100/TÜRKİYE.
Prof.Dr. Kutlu EMRE, Ankara Üniversitesi DTCF Protohistorya ve Önasya Arkeolojisi Anabilim Dalı Sıhhiye/Ankara 06100/TÜRKİYE.
Doç.Dr. Ryoichi KONTANİ, Department of Contemporary Sociological Studies, Notre Dame Seishin University, Japan/JAPAN.
Doç.Dr. Hiroomi TSUMURA, Faculty of Culture and Information Science, Doshisha University, JAPAN
Dr. Sabahattin EZER, Ankara Üniversitesi DTCF Protohistorya ve Önasya Arkeolojisi Sıhhiye/Ankara 06100/TÜRKİYE.

1 Özgüç, T., 1948,"Ankara Üniversitesi Adına Yapılan Fraktin Kazısı ve Tetkik Gezileri-Excavations at Fraktin Near Develi and Researches in Anti-Taurus Region", *Belleten XII/45,* 260-266/266-267; Özgüç, T., 1956,"Fraktin Kabartması Yanındaki Prehistorik Ev/

Kululu, Sultanhanı ve Yassıdağ gibi merkezlerde T. Özgüç ve K. Emre tarafından kazılar gerçekleştirilmiştir[2]. K. Emre başkanlığında gerçekleştirilen "Doğu Kapadokya Araştırma projesi" kapsamında ise, "Karakuyu Hitit Barajı" kazılarak bilim dünyasına tanıtılmıştır[3].

Kayseri'ye komşu illerdeki anıtlar ve önemli merkezler de yine Kültepe ekibi tarafından incelenmiş ve sonuçları yayınlanmıştır[4].

Çalışmalar, sadece Kültepe-Kaniş ile çağdaş dönemlerle ve merkezlerle sınırlı tutulmamış; Kayseri İli sınırları içindeki Türk tarihî açısından çok önemli anıtsal yapılar da ilk kez, Prof.Dr. T. Özgüç tarafından bilim dünyasına duyurulmuştur[5].

Kültepe ekibi dışında bölgede çalışmalar yürüten araştırmacılardan N. Karakaya, Kayseri İli'nin batısında, özellikle Yeşilhisar İlçesi'nde[6], K. Girginer

Prähistorische Haus beim Felsrelief von Fraktin", *Anadolu/Anatolia I*, 59-64.

2 Özgüç, T., 1971, *Demir Devrinde Kültepe ve Civarı/Kültepe and Its Vicinity in the Iron Age. TTKY-V. no 29.* Ankara. Ayrıca, bkz.: Özgüç, T., 1998 "Kululu'da Yeni Bulunmuş Bir Sfenks Başı ve Yazıt Parçası", *Light on Top of the Black Hill Studies Presented to Halet Çambel* (ed. G. Arsebük, M. J. Mellink, W. Schirmer), İstanbul. 615-618; Emre K., 1971, "Sultanhanı Höyüğü'nde 1971-1972 Yıllarında Yapılan Kazılar", *Anadolu/Anatolia, XV*, 87-138. Emre, K., 1973, "Yassıdağ Kazısı 1973" *Anadolu/Anatolia XVII*, 43-72.

3 Emre, K., 1993, "The Hittite Dam of Karakuyu", *Bulletin of the Middle Eastern Culture Center in Japan VII,* 1-17. Araştırma sonucu derlenen malzeme T. Yıldırım tarafından yayınlanmıştır: Yıldırım T., 1998, "Doğu Bölgesi Yüzey Araştırmalarında Derlenen Seramikler", *A.Ü.D.T.C.F. Dergisi Cilt 38, Sayı: 1-2,* 249, 263.

4 Özgüç, T., 1947 "Türk Tarih Kurumu ve Sivas İli Adına Topraktepe'de (Sivas Kalesi) Yapılan Kazı/Die Ausgrabungen von Topraktepe der Burg von Sivas", *Halil Edhem Hatıra Kitabı I.* TTKY VII/5, Ankara, 219-241; Özgüç, T., 1948 "Elbistan Ovasındaki Tetkik Gezileri ve Karahöyük Kazısı"-Archaeological Journeys in the Plain of Ebistan and the Excavations of Karahöyük", *BelletenXII/45*, 226-232/232-237. Komşu Sivas ili ise T. Ökse tarafından gerçekleştirilen bir yüzey araştırması ile araştırılmıştır: Ökse, T., 1994, "Sivas İli 1992 Yüzey Araştırması", *XI. Araştırma Sonuçları Toplantısı, 24 Mayıs-28 Mayıs 1994, Ankara.* Ankara, 243-248; Ökse, T., 1995, "Sivas İli 1993 Yüzey Araştırması", *XII. Araştırma Sonuçları Toplantısı, 30 Mayıs-3 Haziran 1994, Ankara.* Ankara, 317-328.

5 Özgüç, T., 1960" Monuments of the Period of Taşkın Paşa's Principality", *Atti Del Secondo Congresso Internazionale di Arte Turca*, Napoli, 197-201; Özgüç, T., 1962 "Mengücüklere Ait Bir Türbe", *Milli Birlik Türk Sanat Kongresi 19-24.Ekim.1959, Kongreye Sunulan Tebliğler,* Ankara, 325-327; Özgüç, T., Akok, M., 1954, "Melik-Gazi Türbesi ve Kalesi", *Belleten XVIII/71,* 331-336.; Özgüç, T., Akok, M., 1955, "Develi Abideleri", *Belleten XIX/75,* 377-394; Özgüç, T., Akok, M., 1956, "Sarıhan", *Belleten XX/79,* 379-383; Özgüç, T., Akok, M., 1956, "Ağzıkara Han", *Yıllık Araştırmalar Dergisi, Sayı 1,* 93-104; Özgüç, T., Akok, M., 1957, "Alayhan, Öresunhan ve Hızırilyas Köşkü", *Belleten XXI/81,* 139-148; Özgüç, T., Akok, M., 1958, "Üç Selçuklu Abidesi: Dolayhan, Kesikköprü Kervansarayı ve Han Camii", *Belleten XXII/86,* 251-259; Özgüç, T., 1958 Akok, M., "Afşin Yakınındaki Eshab-ı Kehf Külliyesi", *İlahiyat Fakültesi, Türk ve İslam Sanatları Tarihî Enstitüsü,* Ankara, 77-87.

6 Karakaya, N., 2005, 2003 Yılı, Kayseri Yeşilhisar İlçesi Erdemli Köyü'ndeki Kaya Kiliseleri

ise, Erciyes Dağı'nın güneyinde ve kısmen batısında bilimsel araştırmalar gerçekleştirmişlerdir[7].

II. Amaç ve Araştırma Coğrafyası

Assur Ticaret Kolonileri Çağında, merkezi bugünkü K. Irak olan bölgedeki Assur şehri olan krallığın, ticaret için çok sistemli bir ağ kurdukları ve bu ağın Anadolu'daki merkezinin Kültepe olduğu bilinmektedir. Araştırma projesi kapsamında, özellikle M.Ö. II. binyılda Anadolu-Mezopotamya ve Suriye ilişkileri açısından çok önemli bir rol oynayan söz konusu bu ticaret sisteminin gerçekleştiği güzergâhların araştırılması hedeflenmektedir.

Kültepe tabletleri ve arkeolojik buluntular ile birlikte bölgenin coğrafyası ele alındığında, M.Ö. II. binyılda Assur'lu tüccarların Anadolu'ya tek bir yoldan değil, ama farklı güzergâhlardan geldiği düşünülmektedir. Bugünkü bilgilerimiz ışığında bu güzergâhlardan birincisi, Malatya-Sivas/Altınyayla üzerinden, Bünyan İlçesi civarından olmalıdır. İkinci olası güzergâh, Elbistan Ovası'ndan, Sarız-Pınarbaşı ve oradan da Kayseri'ye giden yollarda aranmalıdır. M. Ö. II. binyılda Hitit kralları tarafından yaptırılan "Hitit Kaya Anıtları" ise, olası üçüncü güzergâhı işaret etmektedir. Adana-Kozan-Feke-Tufanbeyli veya Tomarza ve Develi üzerinden Kayseri ve Kültepe'ye gelen yollar, bu anıtların da üzerinde yer aldığı güzergâhtır.

III. 2008 Yılı Çalışmaları

Kültepe-Kaniş kazıları bünyesinde oluşturulan bir ekip tarafından, Kayseri İli sınırları içindeki olası eski ticaret yollarının ve yerleşimlerinin araştırılması konusunda başlatılan "Kayseri Arkeolojik Yüzey Araştırması Projesi" 31.08.2008-29.09.2008 tarihlerinde gerçekleştirilmiştir.

Duvar Resimleri", *22. Araştırma Sonuçları Toplantısı, 24-28 Mayıs 2004, Konya, 2. Cilt.* Ankara, 119-124; Karakaya, N., 2006, "2004 Yılı, Kayseri'nin Yeşilhisar İlçesi Erdemli Vadisi'ndeki Kaya Kiliseleri", *23. Araştırma Sonuçları Toplantısı, 24-28 Mayıs 2004 Konya, 2. Cilt.* Ankara, 113-117; Karakaya, N., 2007, "2005 Yılı, Kayseri'nin Yeşilhisar İlçesi Erdemli Vadisi'ndeki Kaya Yerleşimi Yüzey Araştırması", *24. Araştırma Sonuçları Toplantısı 29 Mayıs-2 Haziran 2006, Çanakkale, 2. Cilt.* Ankara, 501-505

7 Girginer, K.S., vd., 2006, "2004 Yılı Adana ve Kayseri Yüzey Araştırmaları (Sarız ve Kozan), *23. Araştırma Sonuçları Toplantısı 24-28 Mayıs 2004 Konya, 2. Cilt.* Ankara, 293-308; Girginer, K.S., 2007, "2005 Yılı Adana (Ceyhan) ve Kayseri (Develi) Yüzey Araştırmaları, *24. Araştırma Sonuçları Toplantısı 29 Mayıs-2 Haziran 2006 Çanakkale. 2. Cilt.* Ankara, 173-189.

Yüzey araştırmasına Prof.Dr. Kutlu Emre, Doç.Dr. Ryoichi Kontani, Doç.Dr. Hiroomi Tsumura, Arkeolog Gökhan Turan, Arkeolog Sabahattin Ezer, Arkeolog Emrah Çankaya ve öğrenci Michiko Katayama katılmışlardır[8].

Projenin ilk sezonunda veri toplama metotlarının oluşturulması ve gelişmiş bir "*database*" sisteminin kurulması öngörülmektedir. Bu nedenle, arazideki yüzey araştırmalarından ziyade, özellikle dijital ortamda sistemin hazırlanarak Kültepe kazısı ile birlikte ortak bir sunucuda verilerin depolanması ve araştırmacılara sunulabilmesi için teorik ve deneysel çalışmalara ağırlık verilmiştir.

Bu kapsamda, örnek olarak seçilen araştırma güzergâhlarında ve yerleşim alanlarında veri toplama metotları oluşturulmaya çalışılmıştır. Arkeolojik olarak incelenen alanlarda, "mobil total station" ile dijital topografik harita hazırlık modellenmesi ile alanın 360° görüntülenmesi çalışmaları gerçekleştirilmiştir. Ayrıca, GPR yöntemi ile araştırılacak alanların yeraltı radar görüntüleme çalışmaları için ön keşifler yapılmıştır.

---

8 2008 yılı Kayseri arkeolojik yüzey araştırması projesinin gerçekleştirilmesinde katkıları geçen tüm kurum ve kuruluşlar ile yöneticilerine teşekkürlerimi sunarım. Başta Kültür ve Turizm Bakanlığı Kültür Varlıkları ve Müzeler Genel Müdürü Sayın Orhan Düzgün olmak üzere, Kazılar ve Müzeler Dairesi Başkanı Sayın Melik Ayaz, Kazılar Şubesi Müdürü Sayın Gökhan Bozkurtlar ve Kazılar Şubesi Müze Araştırmacısı Şeniz Altunel'e teşekkürlerimi sunarım.
2008 yılı Kayseri arkeolojik yüzey araştırması Projesi T.C. Kültür ve Turizm Bakanlığı DÖSİM Müdürlüğü ile Kayseri Valiliği, Kayseri Büyükşehir Belediyesi Başkanlığı tarafından sağlanan maddi ve lojistik kaynaklarla gerçekleştirildi.
Kayseri Valisi Sayın Mevlüt Bilici çalışmalarımızı her aşamada destekledi. 2008 yılı Kayseri Arkeolojik Yüzey Araştırması Projesi'nin başarıyla tamamlanmasında Sayın Vali Mevlüt Bilici'nin bu desteği önemli bir rol oynadı. Kayseri Valisi Sayın Mevlüt Bilici ve Vali Yardımcıları Sayın Fahri Oluk ve Sayın Mehmet Polat, Sayın Uğur Aladağ ve Sayın Turgay Ergin'e teşekkürlerimi sunarım. Özellikle Sayın Vali Yardımcısı Fahri Oluk'un, Avrupa Birliği projelerinden sağladığı maddî destek, bilimsel çalışmalarımıza yerel yöneticilerin katılımı açısından örnek teşkil etmektedir. Ayrıca, Felahiye ilçesinde gerçekleştirdiğimiz çalışmalarda bize hem maddî hem de manevî açıdan destek veren Felahiye Kaymakamı Sayın Ahmet Gencer'e ekibim adıma teşekkür ederim.
Kayseri Müzesi Müdürlüğü, 2008 yılı Kayseri arkeolojik yüzey araştırması projesinin gerçekleştirilmesi için her türlü katkıyı yaptı. Çalışmalarımızın sağlıklı bir şekilde gerçekleştirilmesini sağlayan Kayseri Müzesi Müdürlüğü'ne başta Sayın Müdür Hamdi Biçer olmak üzere tüm Müze çalışanlarına teşekkür ederim. Bakanlık Uzmanı olarak kazılarımızda görev alan Serdar Okur'un katkıları sayesinde, çalışmalarımız çok daha sağlıklı bir şekilde yürütülebildi. Kendilerine ayrıca teşekkür ederim.

"Kayseri Arkeolojik Yüzey Araştırmaları Projesi" kapsamında 5 höyük ile aşağıda belirtilen yollarda araştırmalar yapılmıştır (Harita: 1):

A. Eski Ticaret Yolları Araştırmaları

1. Kültepe-Sultanhanı-Yassıdagı-Palas-Tuzla Gölü-Sultanhanı Höyük-Kültepe.

2. Kültepe-Bünyan-Hazarşah köyü-Hazarşah-Tuzla Gölü-Kültepe.

3.Kültepe-Güneşli-Höbek-Kızılırmak–Felahiye-Kayapınar-Safrantıkale-Kültepe.

4.Kültepe-Felahiye-Darılı-Kürühüyük-Hacının Tepe-Ziyaret Tepe-Felahiye-Kültepe.

5. Kültepe-Felahiye-Kepiç köy-Yapı –Felahiye-Kültepe.

B. Eski Yerleşim Merkezleri

Bu kapsamda aşağıdaki merkezler incelenmiştir:

1. Dolma Tepe (35°46′32.7″ E-38°54′41.5″ N)

Kayseri İli, Bünyan İlçesi'ne bağlıdır. Bünyan'ın 10 km. güneydoğusunda, Burhaniye Köyü'nden 2 km. uzaklıkta yer almaktadır (Resim: 1). Kültepe'nin 14 km. kuzey doğusundadır. Kayseri- Sivas yolunun tam üzerindedir. Haritada "Dolma Tepe" olarak geçmektedir. Güneybatısında, Sarımsaklı Çayı ve Barajı yer almaktadır. Burada heyet tarafından topografik ölçüm yapıldı (Çizim: 1).

Höyük, 150 metre çapında olup 12 metre yüksekliktedir. Tepe üstünde en az dört kaçak kazı çukur bulunmakta olup en derin çukur ise 3m. den fazladır.

Kalkolitik, Eski Tunç, Assur Ticaret Kolonileri ve Demir Çağına ait seramik parçaları toplanmıştır. Özellikle Eski Tunç Çağına ait parçalar yoğundur (Resim: 2).

2. Hazarşah Höyük (35°58′29.2″E-38°45′29.4″N)

Kayseri İli Bünyan İlçesi sınırları içindedir. Bünyan'ın 13 km.

güneydoğusunda, Hazarşah Köyü'nden 3km. uzaklıktadır (Resim: 3). Kültepe'nin 31 km. doğusundadır. Kayseri-Malatya yolunun üzerindendir. Köylüler tarafından "Çoban Höyük" veya "Hazine" olarak bilinmektedir. Höyük 100 metre çapında ve 16 metre yüksekliktedir.

N. Özgüç[9] ve K. Emre tarafından yapılan "Doğu Kapadokya Yüzey Araştırmaları" sırasında da ziyaret edilmiştir[10].

Burada heyet tarafından topografik ölçüm yapıldı (Çizim: 2).

Höyükte çok sayıda kaçak kazı çukur bulunmaktadır. Özellikle kuzeybatı kısımda oldukça büyük tahribat görülmektedir. Bu çukurun kesitinde sıra halinde taş duvarlar ve kül tabakası görülmektedir. Höyüğün yaklaşık 100 m. batısında 8 m. x 17 m. ölçülerinde taş duvarlı dörtgen planlı bir yapı keşfedilmiştir. Bu yapının içinde bir taş tekne kalıntısı açığa çıkmıştır.

Kalkolitik, Eski Tunç, Assur Ticaret Kolonileri Çağına ait seramik parçaları derlenmiştir. Özellikle Alişar III seramiği dahil Eski Tunç Çağına ait parçalar oldukça yoğundur (Resim:4).

3. Kale Höyük

Kayseri İli, Felahiye ilçe merkezinin tam ortasında bulunan bu höyük, <KKTVKK- 10.12.1988-316> numarası ile tescil edilmiştir (Resim:5). Doğal bir terasın üzerindedir. Kuzeyinde Roma Çağına ait bir çeşme, höyüğün hemen batı kenarında ise Özdere vadisi bulunmaktadır.

Burada heyeti tarafından topografik ölçüm yapıldı (Çizim:3).

Höyüğün üst kısım tıraş edilmiş olup kuzey ve batı kısmı yol ve ev inşaatı nedeni ile tahribata uğramıştır.

Yüzeyde çok az seramik parçası bulunmaktadır. Demir ve Roma Çağına ait seramik parçalarına rastlanmıştır (Resim:6).

9 Özgüç, N., 1947," Kültepe'de Bulunan Hayvan Figürinleri", A.Ü.D.T.C.F. Dergisi Cilt V, Sayı 1, 133-137.

10 Yıldırım T., 1998, "Doğu Bölgesi Yüzey Araştırmalarında Derlenen Seramikler", *A.Ü.D.T.C.F. Dergisi Cilt 38, Sayı: 1-2,* 250.

4. Kuruhüyük

Kayseri İli Felâhiye İlçesi'ne bağlıdır (Resim:7). Felâhiye'nin 10 km kuzeybatısında, Kuruhüyük Köyünün tam içinde yer almaktadır. Kültepe'nin 38 km kuzey batısındadır. Dağ yamacında olup, kuzeybatısında bir vadi yer almaktadır. 40x 63x12m. ölçülerindedir. Tepe, batı ve güneybatı kısım ev inşaat sırasında tahribata uğramıştır. Ayrıca yüzey toprak, traktör ile sürülmüştür.

Yüzeyde Demir ve Roma Çağına ait seramik parçalarına rastlanmıştır (Resim:8).

5. Ziyaret Tepe (35°29'41.2"E-39°08'00.9"N)

<GMEEAYK- 10.02.1983-A-4156> numara ile "Darlı Tümülüsleri" olarak tescillenmiştir. Yörede "Ziraat Mevkii" olarak bilinmektedir.

Felahiye'nin 8 km. kuzeybatısında, Darlı köyünün 1 km. kuzeybatısındadır. Kültepe'nin 33 km. kuzeybatısındadır (Resim: 9). Toplam dört tepeden oluşmaktadır. Burada en büyük tümülüs ile yanında yer alan ikinci tümülüste topografik harita çalışması yapıldı (Çizim: 4). En büyük tümülüs ve üçüncü tümülüs defineciler tarafından tahrip edilmiştir.

Çalışmalarda, tümülüslerin yer aldığı bölgede, olasılıkla günümüzde tamamen tahrip edilmiş bir yerleşim yerine ait Demir Devri malzemeleri ile obsidyen ve sileks malzemeler toplanmıştır.

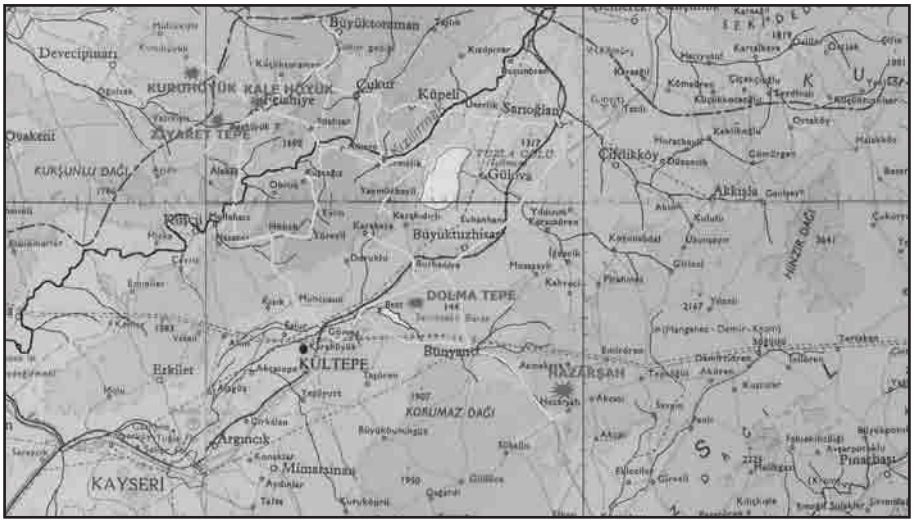

Harita 1: Kayseri Arkeolojik Yüzey Araştırmaları Projesi 2008 çalışma alanı

Resim 1: Dolma Tepe



Resim 2: Dolma Tepe'den derlenen seramikler

Resim 3: Hazarşah Höyük

Resim 4: Hazarşah Höyük'ten derlenen seramikler

Resim 5: Kale Höyük


Resim 6: Kale Höyük'ten derlenen seramikler

Resim 7: Kuruhüyük



Resim 8: Kuruhüyük'ten derlenen seramikler

Resim 9: Ziyaret Tepe

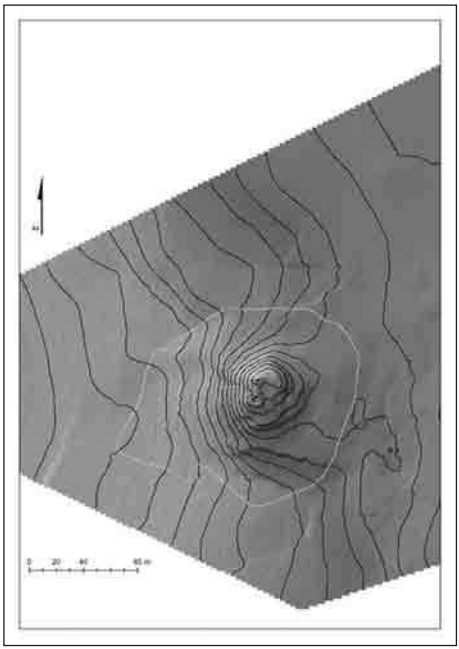

Çizim 1: Dolma Tepe



Çizim 2: Hazarşah Höyük



Çizim 3: Kale Höyük

Çizim 4: Ziyaret Tepe